ANIN
REVISIÓN DE DOCUMENTOS TÉCNICOS
☐ A- ACEPTADO
☐ B- ACEPTADO CON COMENTARIOS
☐ C- RECHAZADO
FIRMA FECHA

ANIN
AUTORIDAD NACIONAL DE INFRAESTRUCTURA

EXPEDIENTE DISEÑO DEFINITIVO – PAQUETE 08

RESUMEN EJECUTIVO

COMPONENTES: 04 - 11.2

500125-CSSP001-000-XX-RP-ZZ-001008-C01

DIRECCIÓN DE INTERVENCIONES MULTISECTORIALES Y DE EMERGENCIA

REV N°	FECHA	DESCRIPCIÓN	ELAB. POR	REV. POR	APROB. POR
R00	16/12/2024	Emitido para Aprobación	O. Hidalgo	O. Hidalgo	D. Kurzawa
R01	25/03/2025	Emitido para Aprobación	O. Hidalgo	P. Arteaga / O. Hidalgo	D. Kurzawa
R02	08/05/2025	Emitido para Aprobación	O. Hidalgo	O. Hidalgo / J. Calle	D. Kurzawa
C01	26/05/2025	Emitido para Construcción	O. Hidalgo	O. Hidalgo / J. Calle	D. Kurzawa
		CARGO:	Jefe de Diseño	Jefe de Diseño/Gestor de Diseño	Gerente del Proyecto
		FIRMAS:	CONSORCIO S&P ING. OMAR HIDALGO AGUILAR JEFE DE DISEÑO CIP N°45727	CONSORCIO S&P ING. OMAR HIDALGO AGUILAR JEFE DE DISEÑO CIP N°45727 CONSORCIO S&P	CONSORCIO S&P ING. DIETHER RODRIGO KURZAWA GERENTE DE PROYECTO CIP. 3289-T

HOJA DE CONTROL DE CAMBIOS

Fecha del cambio	Página Modificada	Razón del cambio	N° de Revisión
16/12/2024	Todas	El contenido del presente documento ha sido generado con la información presentada como parte del expediente Diseño Definitivo – Paquete 05 con código 500125-CSSP001-000-XX-RP-ZZ-001005-R02, con estatus RECHAZADO; por lo tanto, el levantamiento de la matriz de comentarios será subsanado en el desarrollo de este documento.	00
16/12/2024	Todas	El contenido del presente documento ha sido generado con la información presentada como parte del expediente Diseño Definitivo – Paquete 01 con código 500125-CSSP001-000-XX-RP-ZZ-001001-R01, con estatus RECHAZADO; por lo tanto, el levantamiento de la matriz de comentarios será subsanado en el desarrollo de este documento.	00
16/12/2024	Todas	Creación del documento para implementación	00
25/03/2025	6-7-8	Se actualizó las Figura 1, Figura 2 y Figura 4.	01
25/03/2025	10-11	Se actualizó el ítem 5. Metas del proyecto.	01
25/03/2025	12-13	Se actualizó la Tabla 1. Metas del proyecto respecto al perfil.	01
25/03/2025	13-14	Se actualizó la Tabla 2. Resumen de presupuesto	01
25/03/2025	13-14	Se actualizó la Figura 6. Cronograma Diagrama de Gantt – Paquete 08.	01
08/05/2025	Ninguna	El presente documento se procede a remitir sin modificación de fondo, al no encontrar observación en la matriz de comentarios correspondiente a la presente revisión, solo se procede a actualizar la fecha y revisión del presente documento.	02
26/05/2025	Ninguna	Cambio de Estatus de "Emitido para aprobación" a "Emitido para Construcción", incluye cambio de fecha y código de revisión.	C01

TABLA DE CONTENIDO

1. INTRODUCCIÓN 5
2. CARACTERÍSTICAS GENERALES 5
2.1 UBICACIÓN DEL PROYECTO 5
3. OBJETIVOS DEL PROYECTO 8
4. DESCRIPCIÓN TÉCNICA DEL PROYECTO 9
5. METAS DEL PROYECTO 10
6. METAS DEL PROYECTO RESPECTO AL PERFIL 12
7. RESUMEN DE PRESUPUESTO 13
8. MODALIDAD DE EJECUCIÓN 14
9. SISTEMA DE CONTRATACIÓN 14
10. PLAZO DE EJECUCIÓN 15
11. FUENTE DE FINANCIAMIENTO 16

LISTA DE FIGURAS

Figura 1. Área de Influencia del Paquete 08. 6
Figura 2. Área de Influencia del Drenaje Pluvial Urbano Jesús María. 7
Figura 3. Área de Influencia del Canal Jesús María. 7
Figura 4. Ubicación del proyecto: Drenaje Urbano y Canal Jesús María. 8
Figura 5. Esquema de Intervención Jesús María 10
Figura 6. Cronograma Diagrama de Gantt – Paquete 08 15

LISTA DE TABLAS

Tabla 1. Metas del proyecto respecto al perfil 12
Tabla 2. Resumen de presupuesto 13

1. INTRODUCCIÓN

El presente documento tiene como objetivo efectuar la descripción de las obras de drenaje proyectadas a implementar en el Asentamiento Humano Jesús María y la zona rural contigua a pie de laderas correspondiente al paquete 08, del Sector 01. El mismo se enmarca en el Expediente Técnico para la ejecución del "MEJORAMIENTO Y AMPLIACION DEL SERVICIO DE DRENAJE PLUVIAL INTEGRAL DE LA CIUDAD DE TALARA DEL DISTRITO DE PARIÑAS – PROVINCIA DE TALARA – DEPARTAMENTO DE PIURA".

2. CARACTERÍSTICAS GENERALES

2.1 Ubicación del proyecto

El área total del proyecto de drenaje pluvial de Talara abarca 1,726 hectáreas, de las cuales 717 hectáreas se encuentran dentro de la zona urbana y la diferencia pertenece a la zona rural.

El desarrollo del paquete 08 del proyecto se enfoca en áreas urbanas críticas y el control de los flujos provenientes de las zonas rurales para la gestión del drenaje pluvial en Talara.

Drenaje Urbano Jesús María: Esta área se encuentra en la parte baja de Talara y está adyacente a la quebrada Santa Rita. Cubre una superficie de 45.68 hectáreas. El estudio topográfico en esta zona es importante para evaluar las características topográficas específicas y planificar la infraestructura necesaria para gestionar el drenaje pluvial de manera eficaz.

Canal Jesús María: ubicada hacia el este de la zona urbana del Asentamiento Humano Jesús María, Cubre una superficie de 23.28 hectáreas se busca controlar los aportes de flujo provenientes de las laderas contiguas con un canal que conduzca

los flujos hacia las quebradas Santa Rita y Politécnico y evitar el impacto en la zona urbana.

Se ha considerado que esta área es suficiente para el desarrollo de las actividades de ingeniería para el paquete 08, tal como se muestra en la **Figura 1**, como parte integrante del proyecto "Mejoramiento y Ampliación del Servicio de Drenaje Pluvial Integral de la Ciudad". Con lo proyectado, se logrará minimizar los riesgos de inundaciones, lo que permitirá fortalecer la infraestructura de drenaje en la ciudad de Talara – Pariñas.

Figura 1. Área de Influencia del Paquete 08.

Fuente: Elaboración Propia.

Figura 2. Área de Influencia del Drenaje Pluvial Urbano Jesús María.

Fuente: Elaboración Propia.

Figura 3. Área de Influencia del Canal Jesús María.

Fuente: Elaboración Propia.

Figura 4. Ubicación del proyecto: Drenaje Urbano y Canal Jesús María.

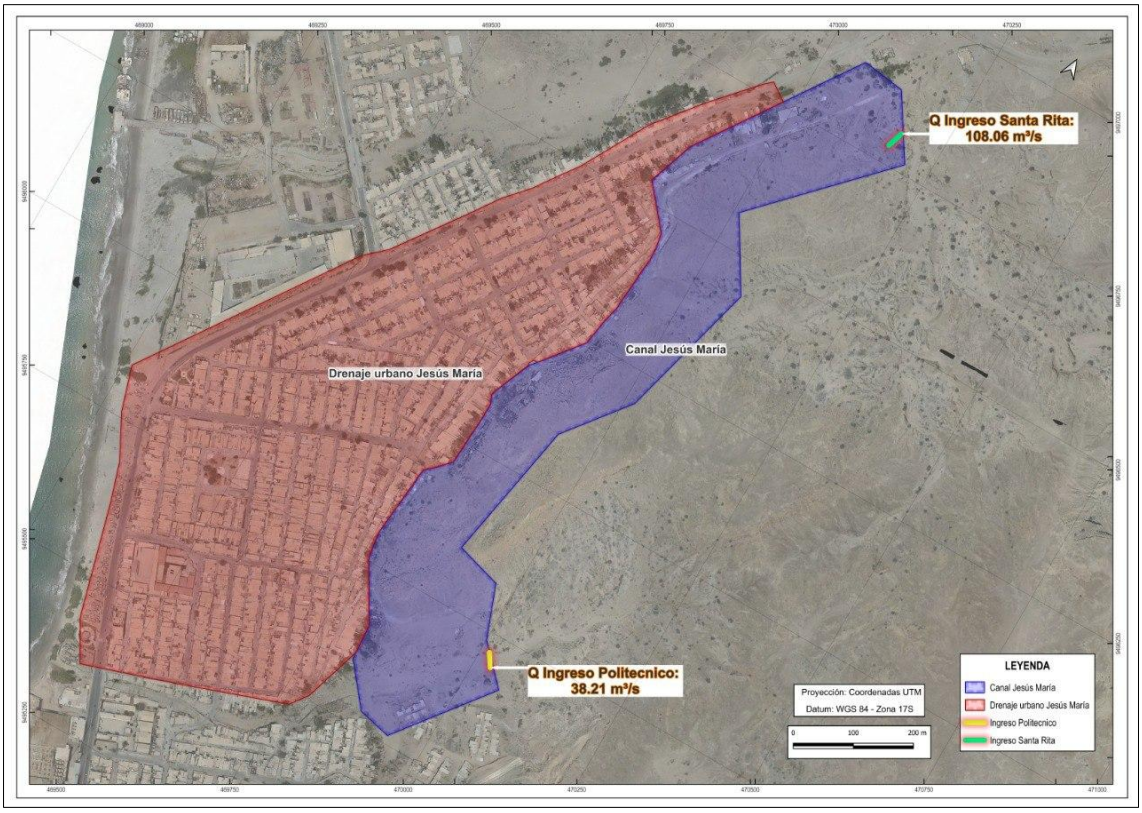

Fuente: Elaboración Propia

3. OBJETIVOS DEL PROYECTO

El objetivo principal del proyecto es alcanzar un mejor nivel socioeconómico de la población en el ámbito urbano del A.H. Jesús María.

Entre los objetivos específicos se encuentran:

- Protección de la población de la zona urbana del A.H. Jesús María de Talara; en riesgo frente a las inundaciones en la situación actual.
- Protección de la infraestructura urbana como carreteras, edificios, viviendas y sistemas de servicios públicos, de los daños causados por inundaciones y exceso de agua.

- Reducción de enfermedades transmitidas producto de las inundaciones y mejora de la seguridad para la comunidad, promoviendo la sostenibilidad urbana.
- Planteamiento y descripción de estructuras de protección (canal de drenaje pluvial) para captar, trasladar y evacuar el flujo de agua y sedimentos, con la finalidad de controlar los peligros de inundación y sedimentación detectados dentro de la zona en estudio.

4. DESCRIPCIÓN TÉCNICA DEL PROYECTO

Para el drenaje pluvial urbano del A.H. Jesús María, Las obras proyectadas en el área consisten en la implementación de una serie de conductos que permitirán la evacuación de excedentes pluviales superficiales hacia el mar. El recorrido de la descarga del flujo estará compuesto por la recolección mediante sumideros, transporte mediante colectores de tubería HDPE Estructurada y la descarga de los fllujos con dirección hacia el mar. Asimismo, se plantea un canal de concreto al pie de laderas que cumpla como protección al área urbana a través de la captación, conducción y evacuación de los flujos de agua y sedimentos.

Figura 5. Esquema de Intervención Jesús María

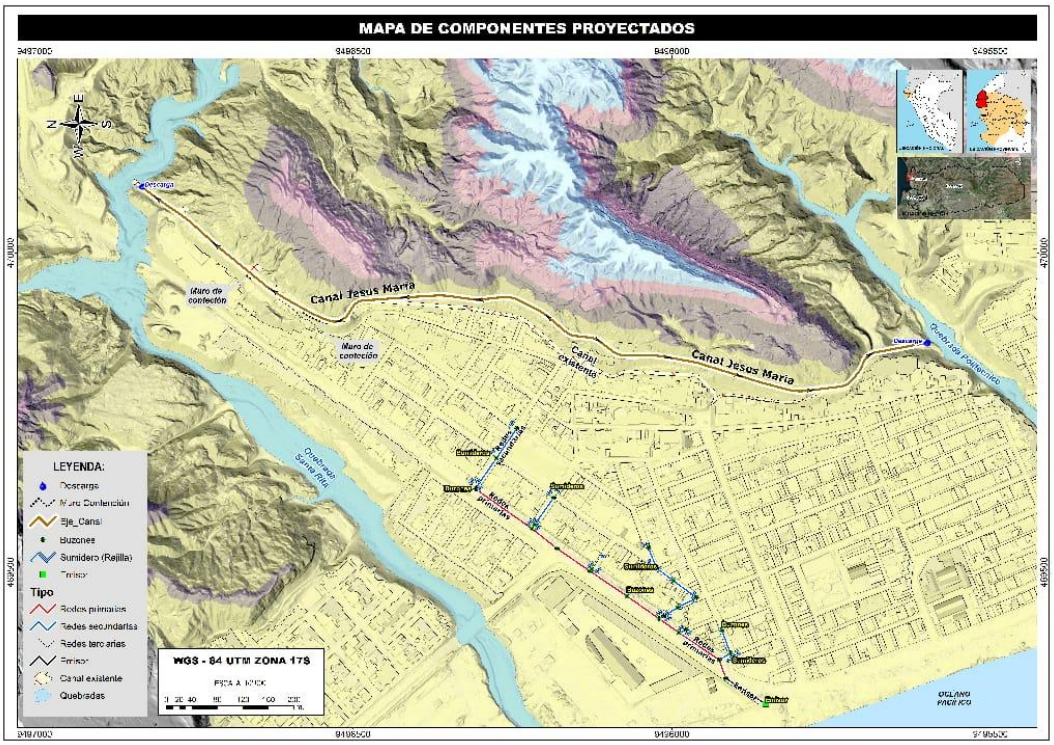

Fuente: Elaboración Propia.

5. METAS DEL PROYECTO

Las metas del proyecto comprenden:

- La Construcción de 01 colector pluvial primario de 498.3m de longitud en la Avenida Antigua Panamericana Norte, mediante la instalación de tubería HDPE-E de diámetros DN1000mm, DN1500mm, DN1600mm y 09 buzones.
- La Construcción de 01 colector pluvial secundario de 641.30m de longitud en la antigua Panamericana Norte, Santa Úrsula, Calle San Agustín, Calle San Felipe, Calle San Francisco, Calle San Ignacio, Calle San Luis, y Calle Santa Rosa; mediante la instalación de tubería HDPE-E de diámetros entre DN450mm, DN500mm, DN600mm, DN700mm, DN800mm y DN900mm, y 19 buzones.
- Construcción de 38 sumideros de rejillas en estructura metálica y con una estructura base de concreto armado. Cuyo ancho estándar es de 1.00 metro y

longitud variable de acuerdo con el tipo de calle. Asimismo, la construcción de colectores terciarios de captaciones de 326.2m de longitud mediante la instalación de tubería HDPE-E de diámetro DN250mm hasta DN375.

- Construcción de 01 emisor de tipo Box de concreto armado de 2.50m x 1.90m.
- Construcción de un canal de forma trapezoidal y rectangular de geometría variable con una divisoria de aguas las cuales descargan hacia la quebrada Santa Rita y Politécnico. El sistema de drenaje por canal está compuesto adicionalmente por 7 aportantes, transiciones de sección y estructuras de descarga; en total se tiene una longitud de 1374.4 metros.
- Tratamiento de Interferencias mediante:

COMPONENTE 04:

Reubicación: 14 postes de media tensión

Reposición: 3 postes de baja tensión **-** Construcción: 1 canal

COMPONENTE 11.2:

REUBICACIÓN:

3 postes redes eléctricas

1 poste de telecomunicación

1 cámara de inspección

1 banco ducto

3 tuberías de oleoducto

REPOSICIÓN

11 tuberías

22 buzones

2 valla metálica

6. METAS DEL PROYECTO RESPECTO AL PERFIL

Tabla 1. Metas del proyecto respecto al perfil

Descripción de productos/acciones		PI VIABLE Formato N° 07-A		Expediente Técnico De Diseño		Medio Fundamental Vinculado	Objetivo del Proyecto
		U. M.	Meta	U.M.	Meta		
1. EFICIENTE Y SUFICIENTE ESTRUCTURA DE RECOLECCION DE LAS AGUAS PLUVIALES URBANO							
1.1.	**Construcción de captación de agua**: Construcción de estructuras de captación: Sumideros	-	-	Und	38	Eficiente y suficiente estructura de recolección de las aguas pluviales urbano	Población de la zona urbana de la ciudad de Talara en riesgo frente a las inundaciones pluviales acceden a servicios eficientes de drenaje pluvial urbano
2. EFICIENTE Y SUFICIENTE INFRAESTRUCTURA DE TRANSPORTE DE AGUA PLUVIAL URBANO							
2.1.	**Construcción de colector de agua pluvial:** Construcción de colectores y subcolectores pluviales en el sector Jesús María	-	-	Km	1.455	Eficiente y suficiente estructura de recolección de las aguas pluviales urbano	Población de la zona urbana de la ciudad de Talara en riesgo frente a las inundaciones pluviales acceden a servicios eficientes de drenaje pluvial urbano
2.2.	**Adecuación de drenes existentes hacia la Qda. Santa Rita – Politécnico: Revestimiento de canal Jesús María**	Km	0.75	Km	1.374	Eficiente y suficiente estructura de recolección de las aguas pluviales urbano	Población de la zona urbana de la ciudad de Talara en riesgo frente a las inundaciones pluviales acceden a servicios eficientes de drenaje pluvial urbano
2.3.	**Construcción de estructuras de protección de drenes en zonas de laderas: Instalación de mallas de protección**	M2	13,800	-	-	Eficiente y suficiente estructura de recolección de las aguas pluviales urbano	Población de la zona urbana de la ciudad de Talara en riesgo frente a las inundaciones pluviales acceden a servicios eficientes de drenaje pluvial urbano
3. EFICIENTE Y SUFICIENTE INFRAESTRUCTURA DE EVACUACIÓN DEL AGUA PLUVIAL URBANO							

Descripción de productos/acciones		PI VIABLE Formato N° 07-A		Expediente Técnico De Diseño		Medio Fundamental Vinculado	Objetivo del Proyecto
		U. M.	Meta	U.M.	Meta		
1. EFICIENTE Y SUFICIENTE ESTRUCTURA DE RECOLECCION DE LAS AGUAS PLUVIALES URBANO							
3.1.	**Estructuras de descarga del canal Jesús María**	--	--	Und	2	Eficiente y suficiente estructura de descarga de las aguas pluviales urbano	Población de la zona urbana de la ciudad de Talara en riesgo frente a las inundaciones pluviales acceden a servicios eficientes de drenaje pluvial urbano
3.2	**Emisor**	-	-	Und	1	Eficiente y suficiente estructura de evacuación de las aguas pluviales urbano	Población de la zona urbana de la ciudad de Talara en riesgo frente a las inundaciones pluviales acceden a servicios eficientes de drenaje pluvial urbano

Fuente: Elaboración Propia.

7. RESUMEN DE PRESUPUESTO

El resumen del presupuesto se presenta a continuación:

Tabla 2. Resumen de presupuesto

ÍTEM	DESCRIPCIÓN	FECHA DEL PPTO: 25/03/2025	
		MONTO (S/)	%
1	**COSTO DIRECTO**	**S/ 36,979,795.89**	
2	**GASTOS GENERALES**	**S/ 6,925,724.02**	**18.73%**
2.01	Gastos Fijos	S/ 93,727.81	0.25%
2.02	Gastos Variables	S/ 6,831,996.21	18.47%
3	**UTILIDAD**	**S/ 2,958,383.67**	**8.00%**
4	**SUB TOTAL**	**S/ 46,863,903.58**	
5	**IGV DEL 18%**	**S/ 8,435,502.64**	**18.00%**
6	**TOTAL PRESUPUESTO INC. IGV**	**S/ 55,299,406.22**	

Fuente: Elaboración Propia.

8. MODALIDAD DE EJECUCIÓN

La modalidad de ejecución del presente paquete es la Tradicional o en cascada: consiste en seguir una secuencia lineal de fases, luego de la aceptación del expediente técnico: planificación, ejecución, pruebas y despliegue. Cada fase se completa antes de pasar a la siguiente; todo esto soportado con BIM, o Building Information Modeling, es una metodología de trabajo colaborativa que utiliza un modelo digital de un edificio para facilitar la planificación, gestión del diseño (previamente aceptado), construcción y gestión de un proyecto.

El proceso constructivo está determinado por la planificación y secuencia lógica de relaciones de actividades en el cronograma.

9. SISTEMA DE CONTRATACIÓN

Los sistemas de contratación a considerar en el proyecto son los siguientes:

- **Precios Unitarios:** Drenaje Pluvial Jesús María componente 11.2 y Canal Jesús María componente 04.
- **Suma Alzada:** Gestión de Tránsito Durante la Ejecución de Obra, Plan de Monitoreo Arqueológico, Intervención Social y Supervisión de Obra.

Dentro del marco normativo D.L. 1192 se establece la modalidad de la ejecución de la liberación de interferencias del proyecto, en el caso del drenaje urbano Jesús María se desarrollará de la siguiente manera:

La reubicación de las Interferencias de Fibra óptica de Telefónica y claro, la ejecutarán ellas mismas y suscribirán un contrato con el consorcio S&P, previa instrucción de la ANIN.

La reubicación de redes eléctricas de propiedad de ENOSA, en este caso, la elaboración del expediente técnico y la ejecución de este se tercerizará a través de un subcontratista, el cual suscribirá un contrato con el consorcio S&P.

La reubicación de redes de agua y alcantarillado de propiedad de EPS GRAU, en este caso, la elaboración del expediente técnico y la ejecución de este se tercerizará a través de un subcontratista, el cual suscribirá un contrato con el consorcio S&P.

10. PLAZO DE EJECUCIÓN

El plazo de ejecución de obra es de 462 días calendarios.

Figura 6. Cronograma Diagrama de Gantt – Paquete 08

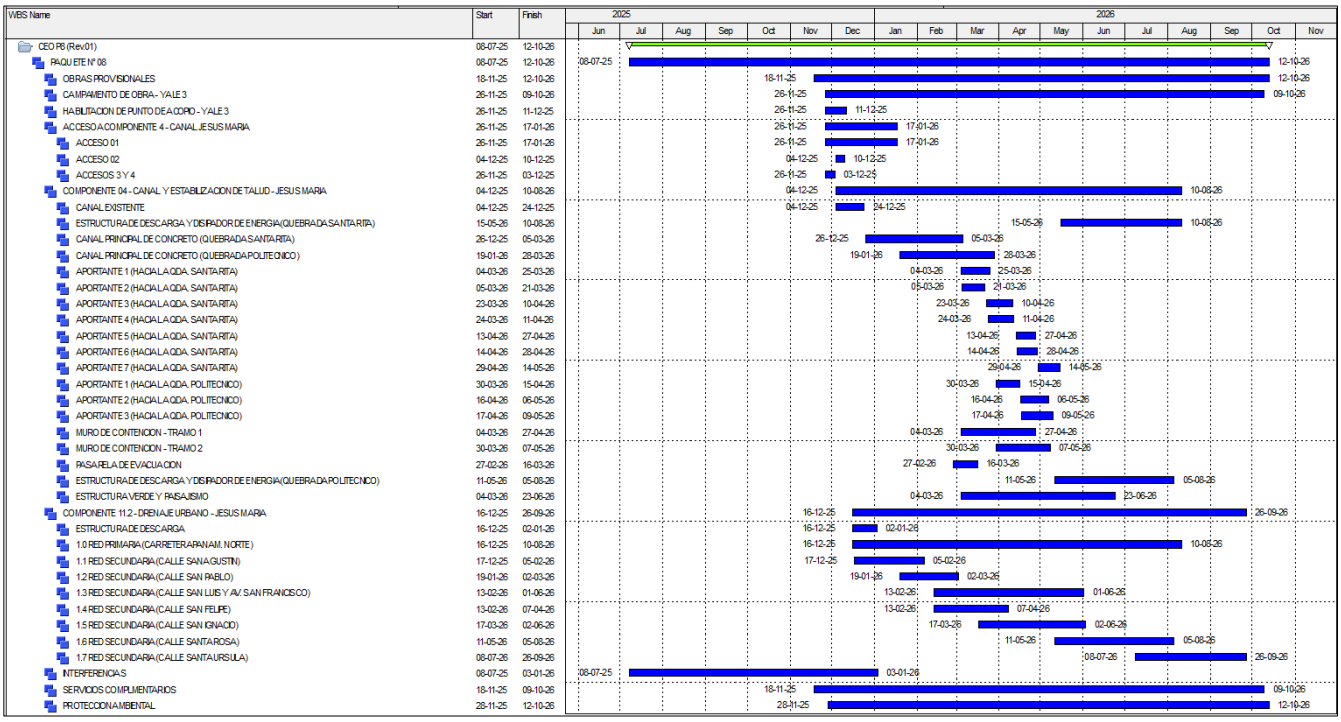

Fuente: Elaboración Propia.

11. FUENTE DE FINANCIAMIENTO

En el marco de la Ley N° 30556, "Ley que aprueba disposiciones de carácter extraordinario para las intervenciones del Gobierno Nacional frente a desastres y que dispone la creación de la Autoridad Nacional de Infraestructura", y con los compromisos asumidos con la Municipalidad de Talara; la Autoridad Nacional de Infraestructura (ANIN) será quien financie el 100% de la ejecución del proyecto, para la cual se prevé ejecutarlo mediante Administración Indirecta (por contrata), a través del Acuerdo G2G, con el Fondo para Intervenciones ante la Ocurrencia de Desastres Naturales (FONDES), creado mediante el artículo 4 de la Ley N° 30458 "Ley que regula diversas medidas para financiar la ejecución de Proyectos de Inversión Pública en apoyo de Gobiernos Regionales y Locales, los Juegos Panamericanos y Parapanamericanos y la ocurrencia de desastres naturales".

Para el cumplimiento de la ejecución del proyecto, la ANIN evaluará la inversión en el marco del Sistema de Programación Multianual y Gestión de la Inversiones, así como gestionar la asignación de los Recursos Financieros para la ejecución del Proyecto, en su condición de UEI (Unidad Ejecutora de Inversiones).